COMUNE DI MORICONE (RM)

PIANO ITALIA 5G – INSTALLAZIONE TORRE INWIT

Torre 5G a Moricone:

cosa è stato deciso, cosa resta aperto, cosa si può ancora fare

Analisi tecnica e territoriale per la comunità di Moricone

Redatto	Marzo 2026 – successivamente alla delibera del Consiglio Comunale del 5 marzo 2026
Comune	Moricone (RM) – circa 2.400 abitanti – Monti Lucretili (Roma)
Oggetto	Installazione di una torre 5G da 30 m nell'area dell'ecocentro comunale – valutazione tecnica, territoriale e contrattuale
Destinatari	Comunità di Moricone, Consiglio Comunale, amministrazione
Natura	Analisi indipendente per i cittadini, basata su dati pubblici ufficiali. Non costituisce parere legale.

La delibera del Consiglio Comunale del 5 marzo 2026 ha individuato l'area dell'ecocentro come sito per la torre. Il contratto con Inwit non è ancora stato firmato. Prima della firma esistono ancora margini concreti: richiedere i dati tecnici mancanti, valutare siti alternativi, negoziare condizioni contrattuali vincolanti. Questo documento analizza tutti questi elementi per informare la comunità e supportare i prossimi passi.

Sommario

1. Introduzione: di cosa stiamo parlando 2
2. Il punto della situazione dopo la delibera 3
3. Il sito proposto: caratteristiche e valutazione 5
4. Gli elementi tecnici ancora aperti 8
5. Le priorità per i prossimi passi: alternative e contratto 9
6. Cosa può e non può fare il Comune: il quadro normativo 16
7. Approfondimento tecnico: mappe, pixel e analisi radio 17
8. Accesso agli atti: i diritti dei cittadini 19
9. Riepilogo 19
10. Fonti e riferimenti 20

1. Introduzione: di cosa stiamo parlando

1.1 Moricone e il problema della connettività mobile

Moricone è un comune di circa 2.400 abitanti sui Monti Lucretili, a circa 50 km da Roma. Come molti piccoli comuni dell'entroterra laziale, soffre di una copertura mobile insufficiente: le reti 4G e 5G, che nelle città sono ormai date per scontate, qui arrivano in modo discontinuo o non arrivano affatto in alcune zone del territorio, in particolare lungo le strade statali che collegano il paese con i centri vicini.

Questa carenza non è solo un disagio per chi vuole usare lo smartphone: riguarda la sicurezza di chi si sposta sul territorio, la possibilità per le imprese agricole di connettersi, la fruibilità del territorio per il turismo e, in prospettiva, l'accesso a servizi digitali sempre più necessari nella vita quotidiana.

1.2 Il Piano Italia 5G: lo Stato finanzia le zone senza copertura

In tutta Italia esistono aree dove gli operatori privati non hanno mai installato antenne, semplicemente perché non sarebbe economicamente conveniente: ci sono troppo poche persone e troppo poche abitazioni per giustificare l'investimento. Queste aree si chiamano 'zone bianche'.

Per colmare questo divario digitale, il governo italiano ha stanziato oltre un miliardo di euro nell'ambito del PNRR (il Piano Nazionale di Ripresa e Resilienza, finanziato dall'Unione Europea dopo il Covid) per due interventi complementari:

- Italia a 1 Giga: porta la fibra ottica fino alle case, per avere internet veloce fisso. A Moricone è già in esecuzione con Open Fiber su 97 civici.
- Piano Italia 5G – Densificazione: installa torri per la copertura mobile nelle zone bianche, in modo che chi si sposta sul territorio abbia segnale. Questo è il piano che riguarda Inwit a Moricone.

I due piani sono distinti e complementari: la fibra porta internet a casa tramite cavo, il 5G copre chi è in movimento. L'arrivo della fibra non elimina la necessità delle antenne, e viceversa.

1.3 Inwit: chi è e cosa fa

Inwit S.p.A. (Infrastrutture Wireless Italiane) è il primo operatore italiano di torri per telecomunicazioni. Non è un operatore telefonico: non vende abbonamenti né gestisce le reti. Il suo lavoro è costruire e gestire le strutture fisiche – i tralicci e i pali – sulle quali i vari operatori (TIM, Vodafone, WindTre, Iliad, ecc.) installano le proprie antenne.

Questo modello si chiama co-location: sulla stessa torre possono coesistere le antenne di più operatori, riducendo il numero totale di infrastrutture necessarie sul territorio. Il guadagno di Inwit dipende dal numero di operatori che affittano spazio sulle sue torri: più operatori ci sono, più Inwit guadagna. Questo ha implicazioni importanti sulla scelta del sito, come spiegheremo più avanti.

Il Piano Italia 5G – Densificazione è stato assegnato tramite gara pubblica. Inwit si è aggiudicata la parte del contratto relativa a circa 1.385 aree bianche in tutta Italia, per un valore di oltre 345 milioni di euro. La scadenza per completare le installazioni è il 30 giugno 2026: dopo quella data, i fondi PNRR non utilizzati devono essere restituiti all'Unione Europea.

1.4 Come viene identificata la zona da coprire

Infratel Italia, la società pubblica che gestisce il programma, ha mappato il territorio nazionale in celle di 100 metri per 100 metri, chiamate pixel. Ogni pixel è classificato in base a cosa c'è dentro (case, campi, strade, boschi) e al livello di copertura mobile che avrà nel 2026. I pixel colorati in viola sulla mappa sono quelli che il Piano Italia 5G deve coprire con fondi pubblici.

Per Moricone, la mappa ufficiale Infratel individua diversi pixel viola lungo il corridoio della SS636, la strada statale che scende verso sud da Moricone. Si tratta prevalentemente di strade e aree rurali, non del centro abitato del paese. Il mandato di Inwit è coprire questi pixel viola: è questo l'obiettivo del bando, non necessariamente portare il 5G dentro al paese.

1.5 Cosa è successo a Moricone: la cronologia

Data	Evento
Luglio 2025	Inwit avvia l'iter per l'installazione a Moricone e propone un primo sito nella zona del Parco Regionale dei Monti Lucretili
Luglio 2025	Il Comune rifiuta il primo sito: ricade all'interno del parco.
Lug.–Dic. 2025	Il Comune individua l'area dell'ecocentro comunale come sito alternativo: terreno pubblico, zona già infrastrutturata (ecocentro e depuratore), distante dal centro abitato *(motivazione rappresentata direttamente dal Sindaco, incontro del 4 marzo 2026)*. La scelta è razionale e consente al Comune di mantenere il controllo negoziale.
Febbraio 2026	Il Sindaco trasmette a Inwit una proposta contrattuale con condizioni (durata pluriennale con opzione di rinnovo). Inwit non ha ancora risposto. *(Informazione acquisita in incontro diretto con il Sindaco, 4 marzo 2026.)*
5 marzo 2026	Il Consiglio Comunale approva con delibera l'area dell'ecocentro come sito per la torre. Il contratto con Inwit non è ancora stato firmato.
Dopo il 5 marzo 2026	Fase di negoziazione contrattuale. Prima della firma definitiva, il Comune ha ancora la possibilità di richiedere dati tecnici, verificare alternative e negoziare condizioni vincolanti.

Cronologia ricostruita sulla base di due fonti verbali: (1) un colloquio diretto con il Sindaco del 4 marzo 2026, da cui provengono le informazioni sui fatti precedenti alla seduta; (2) informazioni riferite da cittadini presenti alla seduta del 5 marzo 2026, alla quale l'autore non ha partecipato direttamente. Nessuna delle due fonti è documentalmente verificabile in questa sede. Le date e la sequenza degli eventi sono da intendersi come indicative.

2. Il punto della situazione dopo la delibera

2.1 Cosa ha deciso il Consiglio e cosa resta aperto

La delibera del 5 marzo 2026 ha compiuto un passo importante: ha individuato l'area dell'ecocentro come sito idoneo per la torre. Questo è il risultato di un percorso avviato nel

luglio 2025, che ha già escluso una prima proposta ritenuta impattante e ha scelto un terreno pubblico, il che è una scelta strategicamente sensata.

Tuttavia la delibera non chiude la partita. Il contratto con Inwit non è ancora stato firmato. Tra la delibera e la firma rimane una finestra – probabilmente breve, data la pressione delle scadenze PNRR – nella quale il Comune conserva ancora la sua leva negoziale più importante.

▲ ATTENZIONE

Secondo quanto emerso nel colloquio del 4 marzo 2026, la proposta contrattuale trasmessa dal Sindaco a Inwit prevede una durata pluriennale con opzione di rinnovo. La durata definitiva sarà quella negoziata e firmata. Qualunque siano le condizioni finali, saranno vincolanti per l'intero periodo. Modificarle in seguito sarà molto difficile. La negoziazione pre-firma è l'unico momento in cui il Comune ha reale potere contrattuale.

2.2 La logica della scelta del Comune: opportunità e rischio

Il Comune ha ragionato in modo comprensibile: se dobbiamo ospitare Inwit, usiamola per portare il 5G anche in paese, non solo sulle strade della SS636. È una logica che trasforma un obbligo normativo in un'opportunità. E scegliere un terreno pubblico garantisce al Comune di restare al tavolo della trattativa.

Questa logica ha però un effetto collaterale che vale la pena rendere esplicito. Un sito comunale ben posizionato, già infrastrutturato e ottimizzato per la copertura del paese, diventa automaticamente attrattivo per la co-location di più operatori nel tempo. Inwit ha tutto l'interesse a caricare sulla stessa torre quanti più operatori possibile – è il suo modello di business. Il risultato è che una torre nata come infrastruttura 5G potrebbe trasformarsi progressivamente in un polo di antenne multiple.

Chi paga questo effetto nel tempo sono le abitazioni nel raggio di poche centinaia di metri: non in termini sanitari – la normativa sui campi elettromagnetici si applica indipendentemente dal numero di operatori – ma in termini di impatto visivo, percezione della qualità del territorio, e potenziale effetto sul valore degli immobili.

2.3 C'è ancora spazio per un sito alternativo?

La delibera ha scelto il sito, ma il contratto non è firmato. Prima della firma, il Comune può legittimamente richiedere una simulazione radio comparativa tra il sito dell'ecocentro e un sito alternativo. Non si tratta di rimettere in discussione il voto, ma di completarlo con i dati tecnici che al momento della delibera non erano disponibili.

Se la simulazione comparativa mostrasse un sito alternativo tecnicamente superiore – in particolare un sito in quota più elevata che consenta una torre più bassa per la stessa copertura – il Comune avrebbe elementi concreti per riconsiderare. La giurisprudenza recente (TAR Lombardia, Ord. 266/2025) conferma che questa è una richiesta legittima e non ostruzionistica.

◆ VALUTAZIONE TECNICA

Un sito più elevato rispetto all'ecocentro (182 m s.l.m.) garantirebbe margini radioelettrici superiori verso la zona bianca (259–287 m s.l.m.) e potrebbe consentire una torre di altezza inferiore per ottenere la stessa copertura. Struttura più bassa = minore impatto visivo = maggiore compatibilità paesaggistica. Questo è un argomento urbanistico concreto, indipendente dall'esito della simulazione. Si precisa che l'analisi della linea di vista (LOS) contenuta in questo documento è un'analisi geometrica preliminare: non è una simulazione radio e non dimostra la copertura effettiva, che dipende da parametri che solo una simulazione DTM professionale può quantificare.

3. Il sito proposto: caratteristiche e valutazione

3.1 Posizione e quote

L'ecocentro si trova in località Crocetta, a ovest del centro abitato, in una depressione del terreno a 182 m s.l.m. Il centro del paese è sulla cresta collinare a nord-est, a 296 m. La zona bianca da coprire si trova a est/sudest, lungo la SS636, a quote tra 259 e 287 m.

Punto	Coordinate (WGS84)	Quota s.l.m.
Ecocentro comunale (sito individuato dalla delibera – contratto non firmato)	42.111788°N, 12.762149°E	182 m
Centro abitato – Piazza del Comune	42.116618°N, 12.773652°E	296 m
Prima proposta Inwit (area parco – rifiutata dal Comune)	posizione indicativa (1)	~272 m (1)
Pixel viola più a nord (SS636, zona bianca)	42.111188°N, 12.774726°E	287 m
Pixel viola più a sud (SS636, zona bianca)	42.104213°N, 12.773494°E	259 m

Coordinate: Google Maps/Earth (WGS84). Verde = sito approvato. Viola = zona bianca target. (1) La posizione e la quota del primo sito proposto da Inwit sono indicative, ricavate da una mappa mostrata nel colloquio del 4 marzo 2026 con il Sindaco; non sono state verificate su fonte ufficiale.

Vale la pena notare che il primo sito proposto da Inwit si trovava in posizione più elevata e più vicina alla zona bianca rispetto all'ecocentro (quota stimata ~272 m s.l.m., secondo quanto indicato nel colloquio del 4 marzo 2026). Il rifiuto del Comune è stato motivato, secondo quanto riferito nel colloquio del 4 marzo 2026, con i vincoli del Parco Regionale dei Monti Lucretili.

3.2 La geometria del territorio: dove è cosa

La disposizione geografica dei punti chiave è ben visibile nelle mappe seguenti. L'aspetto più importante da capire è che il centro abitato di Moricone non si trova tra l'ecocentro e la zona bianca: il paese è a nord-est, il percorso radioelettrico dalla torre alla SS636 scorre più a sud, senza che il paese faccia da ostacolo.

Per leggere le mappe: l'unico colore rilevante ai fini di questo documento è il **Viola**

- **Viola**: **zone bianche target del Piano Italia 5G** — strade e aree rurali lungo la SS636, finanziamento PNRR
- **Rosa chiaro**: aree urbane con abitazioni — intervento privato, non PNRR
- **Giallo/arancione**: aree agricole e non abitate
- **Linea nera**: confine del territorio comunale

Fig. 1 – Vista d'insieme dell'area di Moricone con la mappatura Infratel 2024. Viola: zone bianche target del Piano Italia 5G lungo la SS636. Rosa: area urbana con intervento privato (non PNRR). Giallo/arancione: aree agricole e non abitate. Linea nera: confine del comune di Moricone. Fonte: Infratel Italia, Mappatura Mobile 2024.

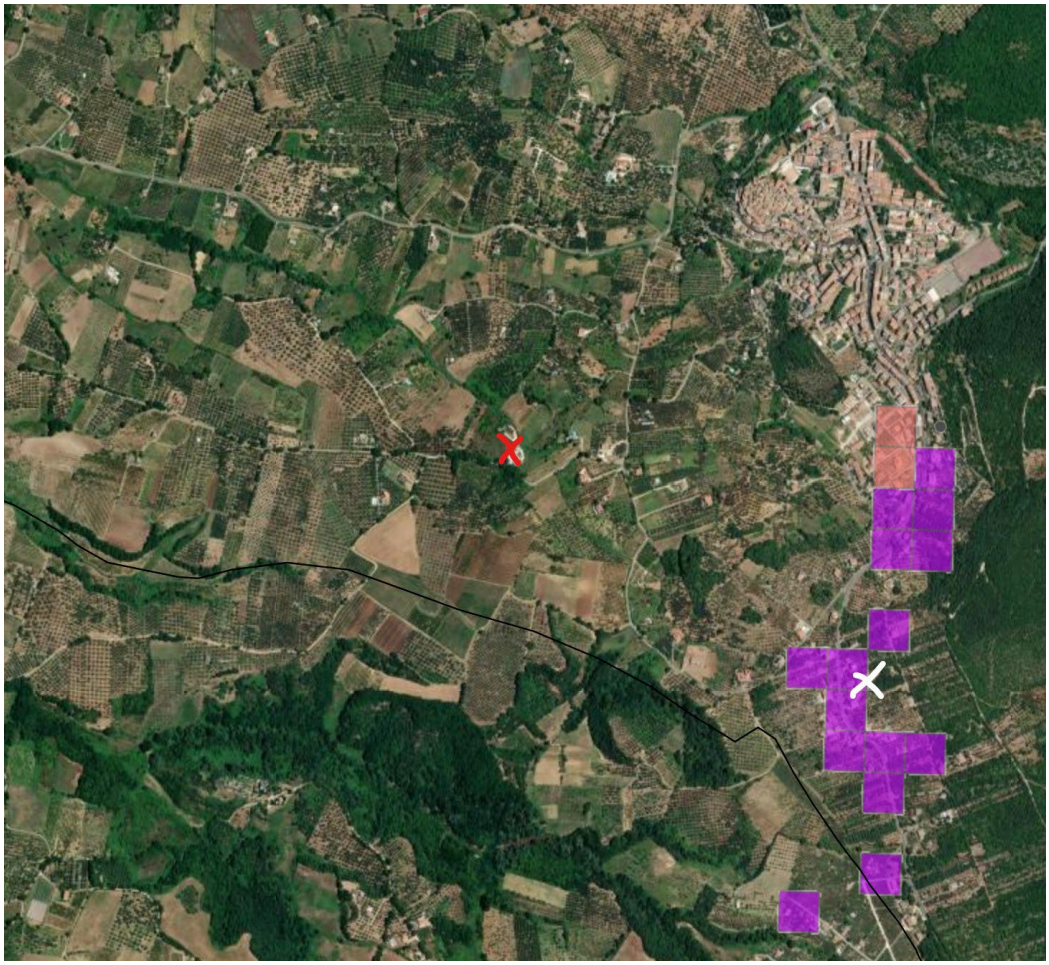

Fig. 2 – Dettaglio dell'area con i siti principali. X rossa: ecocentro comunale, sito individuato dalla delibera del 5 marzo 2026 (contratto non ancora firmato) – coordinate 42.111788°N, 12.762149°E, quota 182 m (da Google Maps/Earth). X bianca: posizione indicativa del primo sito proposto da Inwit – ricavata da una mappa mostrata nel colloquio del 4 marzo 2026 con il Sindaco; le coordinate non sono state verificate su fonte ufficiale, la quota ~272 m è una stima orientativa. Rifiutato dal Comune; la motivazione riferita nel colloquio del 4 marzo 2026: vincoli del Parco Regionale dei Monti Lucretili. Pixel viola: zona bianca target lungo la SS636. Fonte mappa di sfondo: Infratel Italia, Mappatura Mobile 2024.

3.3 Il problema del dislivello

Il dato più rilevante dal punto di vista tecnico è il dislivello tra il sito proposto e i pixel da coprire. La cima di una torre da 30 m installata all'ecocentro si troverebbe a 182 + 30 = 212 m s.l.m. I pixel della zona bianca si trovano tra 259 e 287 m s.l.m.: sono significativamente più alti della cima della torre.

Il dislivello tra il sito e i pixel target è strutturalmente sfavorevole: una torre installata più in basso rispetto alle aree da coprire opera in condizioni radioelettriche peggiori rispetto a un sito in quota equivalente o superiore.

◆ VALUTAZIONE TECNICA

Qualora la simulazione DTM professionale evidenziasse la necessità di una torre di altezza superiore ai 30 m annunciati, l'impatto visivo sarebbe maggiore di quanto attualmente prospettato. Un sito in quota più elevata consentirebbe una struttura più bassa a parità di copertura. Questo è l'argomento urbanistico più solido per richiedere una simulazione

comparativa prima della firma.

3.4 La vicinanza alle abitazioni

Il sito dista poche centinaia di metri dalle prime abitazioni. La normativa italiana non prevede distanze minime obbligatorie tra le antenne e le case — i tribunali lo hanno ribadito più volte — e questo documento non intende usare questo argomento in chiave sanitaria.

Il punto è di natura diversa. Come illustrato in dettaglio nella sezione 5.2, il Comune ha già adottato esplicitamente la vicinanza alle abitazioni come criterio di esclusione nel proprio processo valutativo. Questo criterio merita di essere applicato con coerenza anche al sito attualmente individuato, dove alcune abitazioni si trovano nel raggio di circa 200 metri.

La co-location nel tempo rafforzerebbe questo problema: come spiegato nella sezione 2.2, una torre ottimizzata per la copertura del paese diventa automaticamente attrattiva per operatori aggiuntivi. Il criterio di tutela che il Comune ha già applicato ad altri siti dovrebbe valere anche qui — e con maggiore rigore proprio perché il rischio di espansione dell'infrastruttura nel tempo è più alto.

4. Gli elementi tecnici ancora aperti

4.1 Dove arriva la fibra?

Una torre 5G ha bisogno di un collegamento di backhauling per trasportare i dati verso la rete internet. Questo collegamento può essere realizzato tramite fibra ottica o tramite ponte radio a microonde. La fibra è la soluzione tecnicamente superiore per capacità, latenza e affidabilità — ed è quella che il programma PNRR ha già realizzato sul territorio con FiberCop. Per Moricone, il piano Italia 5G – Backhauling (realizzato da FiberCop, codice I-BH-LAZ-05541) risulta completato: 1 sito realizzato.

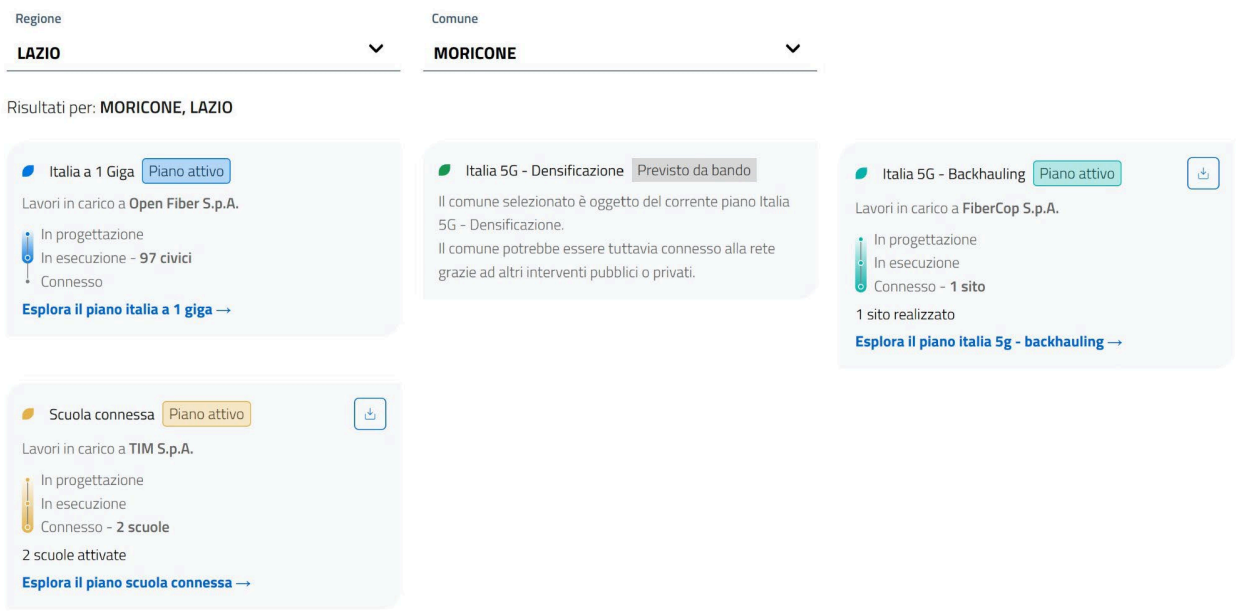

Fig. 4 – Stato dei piani PNRR per il Comune di Moricone (fonte: connetti.italia.it). Italia 5G – Densificazione: 'Previsto da bando' (non ancora contrattualizzato). Italia 5G – Backhauling: piano attivo, 1 sito realizzato. Italia a 1 Giga: piano attivo, 97 civici in esecuzione.

? ELEMENTO DA VERIFICARE

I dati pubblici non indicano dove si attesta fisicamente la fibra di FiberCop nel territorio comunale. Non è verificabile se il collegamento raggiunga già l'area dell'ecocentro o si fermi nel centro abitato. Se la fibra non arriva all'ecocentro, sarà necessario realizzare un raccordo aggiuntivo con costi a carico dell'operatore. Questo elemento potrebbe influire sulla preferenza stessa di Inwit per il sito.

→ CONSIDERAZIONE STRATEGICA

Il Comune ha interesse a chiedere formalmente a Inwit dove si attesta il backhauling prima di firmare il contratto. Se la fibra fosse attestata vicino alla SS636 più che all'ecocentro, un sito alternativo più prossimo alla zona bianca potrebbe risultare più conveniente anche per Inwit – modificando la dinamica negoziale a favore del Comune.

4.2 La simulazione radio: dato obbligatorio, non ancora depositato

I profili altimetrici analizzati in questo documento (sezione 7) indicano in via preliminare l'assenza di ostacoli fisici significativi tra il sito e la zona bianca, sulla base dei dati SRTM 30m disponibili. Questo è un dato necessario ma non sufficiente: non sostituisce una simulazione radio professionale.

Una simulazione completa tiene conto del tipo specifico di antenna, del tilt verticale (l'angolazione dell'antenna verso il basso, che determina dove cade il segnale), della potenza di trasmissione e della morfologia dettagliata del terreno. Solo con questi dati si può stabilire con certezza l'altezza minima necessaria e la copertura effettiva.

? ELEMENTO DA VERIFICARE

La simulazione DTM deve essere prodotta da Inwit nell'ambito del procedimento autorizzativo ex art. 87 D.Lgs. 259/2003, che richiede l'accertamento ARPA della compatibilità elettromagnetica del progetto ai sensi della L. 36/2001 e del DPCM 8 luglio 2003. Il Comune deve richiedere che venga depositata agli atti prima della firma del contratto, non dopo. Deve includere sia il sito dell'ecocentro sia almeno un sito alternativo comparativo.

5. Le priorità per i prossimi passi: alternative e contratto

La delibera ha individuato un sito. Prima della firma il Comune conserva ancora due leve concrete: la valutazione di siti alternativi e la negoziazione delle condizioni contrattuali. Entrambe meritano di essere usate con piena consapevolezza tecnica. Un contratto mal negoziato è vincolante per l'intera durata contrattuale.

5.1 Prima della firma: le condizioni imprescindibili

1. Richiedere a Inwit il tracciato e il punto di attestazione del backhauling FiberCop
2. Richiedere la simulazione di copertura con DTM reale per il sito ecocentro, con indicazione dell'altezza minima effettivamente necessaria

3. Richiedere una simulazione comparativa per almeno un sito alternativo lungo la SS636 o in quota superiore
4. Depositare tutti questi documenti agli atti prima della firma

→ CONSIDERAZIONE STRATEGICA

Queste non sono richieste ostruzionistiche: sono dati tecnici che il Comune ha il diritto e il dovere di conoscere prima di firmare un contratto di lunga durata. Inwit è tenuta a produrli nell'ambito del procedimento autorizzativo. Richiederli prima della firma è un atto di buona amministrazione.

5.2 Il sito alternativo: un diritto del Comune e un dovere verso i cittadini

La delibera ha individuato un sito. Prima della firma esiste ancora la possibilità di richiedere una simulazione comparativa e di riconsiderare il sito. Questo non significa rimettere in discussione il voto: significa completarlo con i dati tecnici che al momento del voto non erano disponibili. Le condizioni che si negoziano ora resteranno vincolanti per l'intera durata contrattuale.

Il criterio già applicato dal Comune

Secondo quanto riferito da partecipanti alla seduta del 5 marzo 2026, nel corso del processo di selezione il Comune ha valutato e scartato diversi siti — di proprietà pubblica — ritenendo inaccettabile la loro vicinanza alle abitazioni. Il criterio applicato è stato esplicito: **la presenza di case nelle immediate vicinanze esclude un sito.**

L'ecocentro si trova nel raggio di circa 200 metri dalle prime abitazioni. Un criterio introdotto dal Comune nel proprio processo valutativo merita di essere applicato con coerenza — non è questo documento a sostenerlo: è il Comune che lo ha già stabilito.

La classificazione urbanistica non esime dalla tutela dei residenti

Secondo quanto dichiarato dal Sindaco nel colloquio del 4 marzo 2026, l'area dell'ecocentro ricade in una "zona a servizi" — classificazione che, sempre secondo il Sindaco, precede le costruzioni residenziali sorte nelle immediate vicinanze. Questa indicazione non è stata verificata su atti ufficiali ai fini del presente documento.

La questione, tuttavia, non riguarda la cronologia urbanistica. Le abitazioni esistenti sono parte del contesto insediativo reale, sviluppatosi in modo regolare. La destinazione d'uso di un'area descrive cosa vi si può costruire, non esime il Comune dall'obbligo istituzionale di considerare chi ci vive accanto.

Chi ha edificato in quella zona lo ha fatto legittimamente, in un contesto che all'epoca non prevedeva un'infrastruttura di questo tipo. La classificazione "zona a servizi" protegge il diritto del Comune a installare servizi: non autorizza a ignorare i residenti.

Il Comune ha il dovere di proteggere la qualità del paesaggio e dell'ambiente vissuto dai residenti.

I siti alternativi esistono

I vincoli esistenti sui siti già esaminati sono reali: il crinale est ricade nel parco, il cimitero risulta otticamente schermato dal paese dalla morfologia del terreno. Ma in un territorio prevalentemente rurale come quello di Moricone, con ampie aree aperte e non edificate, la disponibilità di siti alternativi non si esaurisce nei casi già esaminati.

Il criterio rilevante per individuare un sito idoneo è la combinazione di due elementi oggettivi: distanza sufficiente dalle abitazioni e quota che consenta la copertura dei pixel target con una struttura di altezza contenuta. Un sito con queste caratteristiche potrebbe esistere in più punti

del territorio, incluse aree agricole o di servizio non comunali, e meriterebbe di essere verificato con una simulazione comparativa prima della firma.

La simulazione comparativa: completare la delibera, non smentirla

Se la simulazione comparativa evidenziasse un sito alternativo tecnicamente superiore — in particolare uno a quota più elevata, che consenta una struttura di altezza inferiore per la stessa copertura e a maggiore distanza dalle abitazioni — il Comune avrebbe elementi tecnici concreti per riconsiderare prima della firma. Non si tratterebbe di rimettere in discussione la delibera del 5 marzo: si tratterebbe di **completarla con i dati tecnici che al momento del voto non erano disponibili.** Se le condizioni sostanziali restano invariate, non è necessaria una nuova delibera.

◆ IN SINTESI

Il Comune ha già stabilito il proprio criterio: la vicinanza alle abitazioni conta. Quel criterio si applica anche all'ecocentro. La simulazione comparativa è lo strumento per verificare se esiste un sito che rispetta quel criterio meglio dell'attuale scelta. Richiederla prima della firma non è ostruzione: è coerenza.

→ PUNTO CHIAVE

Il Comune si trova di fronte a una scelta concreta: individuare un sito alternativo a maggiore distanza dalle abitazioni, oppure confermare il sito dell'ecocentro assumendosi l'impegno contrattuale e autorizzativo di tutelarne i residenti. Entrambe le strade sono percorribili. Nessuna delle due si percorre senza una scelta consapevole.

5.3 Proprietà del terreno o potere regolatorio?

Nel processo di selezione del sito, la proprietà pubblica del terreno è emersa come criterio prioritario — con l'argomento che solo in questo modo il Comune potrebbe mantenere adeguata capacità di controllo sull'infrastruttura, e che affidare la scelta a un privato aprirebbe la strada a soluzioni più impattanti. Questo ragionamento merita di essere esaminato con attenzione, perché confonde due ruoli che il Comune esercita in modo distinto e indipendente.

Il ruolo di proprietario del terreno riguarda il contratto di locazione: il Comune negozia le clausole e può inserirvi condizioni di tutela. **Il ruolo di autorità regolatoria** riguarda il permesso di costruire: il Comune lo rilascia — o lo nega — e può imporre condizioni urbanistiche vincolanti su qualunque sito nel territorio comunale, pubblico o privato. Altezza massima della struttura, criteri paesaggistici, prescrizioni sulla co-location, obbligo di monitoraggio ARPA: tutte queste condizioni derivano dal secondo ruolo, non dal primo. **Un sito privato non sottrae al Comune nessuno di questi strumenti.**

Lo stesso legale specializzato in diritto amministrativo e telecomunicazioni la cui consulenza è raccomandata prima della firma del contratto potrebbe essere incaricato di definire le prescrizioni autorizzative da applicare a un sito privato, con effetti analoghi in termini di controllo sull'infrastruttura. Il potere regolatorio del Comune vale su tutto il territorio comunale: non dipende da chi possiede il terreno.

5.4 Le clausole contrattuali da negoziare

Se il sito dell'ecocentro venisse confermato, le clausole contrattuali sarebbero lo strumento principale di tutela del territorio per l'intera durata contrattuale. Le clausole si articolano in tre gruppi: struttura fisica, tecnologie future, e controllo elettromagnetico.

A — Struttura fisica

- Altezza massima della struttura vincolante nel contratto: impedisce sopraelevazioni future senza consenso esplicito del Comune.
- Limite dell'ingombro fisico degli apparati in quota: superficie di sagoma e peso massimo degli apparati installabili, per evitare che la torre si carichi progressivamente senza che il Comune ne abbia formale contezza.
- Obbligo di collegamento tramite dorsale in fibra ottica: la dorsale FiberCop è già presente sul territorio, finanziata con fondi pubblici nell'ambito del Piano Italia 5G – Backhauling. È la soluzione tecnicamente superiore per capacità, latenza e affidabilità. Il contratto deve escludere esplicitamente l'uso di ponti radio come soluzione alternativa di backhauling, garantendo coerenza con l'investimento pubblico già realizzato sul territorio.
- Diritto di rinegoziazione a ogni rinnovo (fondamentale nel contratto pluriennale con opzione di rinnovo, secondo la proposta del Sindaco).

B — Tecnologie future: vincolo parametrico invece che tecnologico

La torre viene realizzata nell'ambito del Piano Italia 5G con fondi PNRR: il 5G è la tecnologia di riferimento e il punto di partenza. Il contratto dovrebbe stabilire esplicitamente che tecnologie precedenti al 5G non rientrano nel perimetro e non possono essere installate in regime di co-location.

Per le evoluzioni future, un vincolo per nome di tecnologia presenterebbe due criticità strutturali: escluderebbe tecnologie più efficienti che emergeranno nel corso della durata contrattuale, e sarebbe facilmente aggirabile attraverso la ridenominazione commerciale degli apparati. Un'antenna 5G Advanced o un nodo 6G potrebbe non ricadere formalmente nella definizione contrattuale di "5G".

Il vincolo da inserire in contratto dovrebbe riguardare i parametri oggettivi dell'impianto, non il nome della tecnologia. Il Comune non ha interesse a sapere come si chiama la tecnologia installata: ha interesse a controllare l'impatto fisico nel tempo. Un vincolo parametrico è tecnologicamente neutro verso il futuro — segue l'impianto indipendentemente da come evolvono gli standard, senza richiedere aggiornamenti contrattuali ad ogni nuova generazione di tecnologia.

I tre parametri vincolanti:

Parametro	Contenuto della clausola
Potenza radiata equivalente cumulativa (EIRP)	Tetto massimo di potenza cumulativa per tutti gli operatori presenti sulla torre, espresso in watt EIRP. Non può essere superato senza nuova valutazione ARPA e parere favorevole del Comune. Se il 6G è più efficiente userà meno potenza e rientrerà automaticamente nel limite; se una nuova tecnologia fosse più energivora, verrebbe bloccata.
Numero massimo di operatori in co-location	Numero massimo di operatori contemporaneamente presenti (es. 3). Ogni aggiunta oltre la soglia richiede nuova valutazione cumulativa

	ARPA depositata agli atti comunali, indipendentemente dalla tecnologia utilizzata.
Ingombro fisico degli apparati	Superficie di sagoma e peso massimo degli apparati in quota, espressi in m² e kg. Impedisce che la torre si carichi di apparecchiature aggiuntive che ne modifichino visivamente il profilo senza intervento del Comune.

Definizione contrattuale di "variazione migliorativa":

Una sostituzione tecnologica (inclusa la transizione al 6G o tecnologie successive) è ammessa in regime semplificato — sola comunicazione al Comune, senza nuova autorizzazione — se e solo se soddisfa tutte e tre le seguenti condizioni:

- Potenza EIRP cumulativa dell'impianto invariata o ridotta rispetto alla configurazione autorizzata
- Ingombro fisico degli apparati invariato o ridotto
- Nessun operatore aggiuntivo rispetto alla configurazione in essere

Se anche una sola condizione non è rispettata, la modifica rientra nel regime ordinario: nuova valutazione preventiva ARPA, deposito agli atti comunali, parere favorevole del Comune prima di qualsiasi intervento.

→ **CONSIDERAZIONE STRATEGICA**

Questa impostazione parametrica è più solida di qualsiasi vincolo tecnologico nominale: segue l'impianto per tutta la sua vita contrattuale indipendentemente da come si evolveranno gli standard di telecomunicazione.

Il Comune dimostra apertura all'innovazione — non blocca il 6G a priori — ma mantiene il controllo sull'impatto fisico ed elettromagnetico. Questa posizione è anche giuridicamente più difendibile in caso di contenzioso.

C — Canone e benefici comunitari

- Canone equo: almeno 2.000–5.000 €/anno indicizzato ISTAT, non il solo Canone Unico Patrimoniale (~800 €).
- Corrispettivo aggiuntivo per ogni operatore in co-location, nei limiti consentiti dalla clausola parametrica.
- Benefici comunitari a carico di Inwit: connettività fisica (fibra o equivalente) per le abitazioni limitrofe all'area dell'ecocentro; ripristino del manto stradale nell'area di cantiere e nel raggio di almeno 1 km dal sito.

Il contesto infrastrutturale delle abitazioni limitrofe

L'arrivo di un'infrastruttura di interesse pubblico nell'area dell'ecocentro è l'occasione per portare all'attenzione dell'amministrazione problemi preesistenti che riguardano le abitazioni circostanti e che non dipendono da Inwit: discontinuità nell'erogazione dell'acqua pubblica, riconducibile alla vicinanza con il depuratore comunale; criticità nella rete elettrica aerea, sottodimensionata per la zona; degrado del manto stradale nell'area più ampia, oltre il perimetro coperto dagli obblighi contrattuali di Inwit.

Questi problemi non sono negoziabili con Inwit e non rientrano nelle clausole contrattuali. Sono tuttavia parte del contesto in cui si inserisce l'infrastruttura, e la loro soluzione è un impegno che l'amministrazione comunale può assumere in modo autonomo, indipendentemente dall'esito della negoziazione con Inwit.

▲ ATTENZIONE

Il contratto dovrebbe essere valutato da un legale specializzato in diritto amministrativo e telecomunicazioni prima della firma. Una clausola penalizzante oggi può essere impossibile da modificare per l'intera durata contrattuale.

5.5 Separare chiaramente i due obiettivi

Il Comune sta perseguendo due obiettivi distinti, che è opportuno riconoscere esplicitamente:

- Obiettivo del bando PNRR: coprire le zone bianche della SS636 (strade e aree rurali).
- Obiettivo aggiuntivo del Comune: portare copertura 5G anche nel centro abitato.

Questi due obiettivi possono convergere o divergere a seconda del sito scelto e dell'altezza della torre. Se il Comune intende perseguire entrambi, è corretto farlo esplicitamente e con piena consapevolezza delle implicazioni. Se invece si privilegiasse l'obiettivo del bando, la scelta del sito e le clausole contrattuali (in particolare i parametri di impianto) cambierebbero di conseguenza.

5.6 Il ruolo di ARPA Lazio: cosa garantisce la legge e cosa dovrebbe negoziare il Comune

Le clausole di monitoraggio elettromagnetico inserite nel contratto dovrebbero essere calibrate su quello che ARPA Lazio già fa per legge e su quello che invece non è garantito automaticamente. Confondere i due piani porta a clausole ridondanti o, peggio, a lacune che resteranno aperte per l'intera durata contrattuale.

Il percorso ARPA in due fasi obbligatorie

Fase 1 — Parere preventivo (prima dell'installazione)

Obbligatorio per legge ai sensi dell'art. 87 D.Lgs. 259/2003. Il Comune autorizza la costruzione dell'impianto, ma l'accensione è subordinata al parere positivo di ARPA Lazio, che costituisce un procedimento autonomo. ARPA valuta:

- La simulazione previsionale del campo elettromagnetico prodotto da tutti gli impianti già autorizzati nella zona, ipotizzando che tutti funzionino contemporaneamente alla massima potenza (criterio cautelativo).
- Il rispetto del limite di esposizione (20 V/m) e soprattutto del valore di attenzione, aggiornato dalla L. 214/2023 a 15 V/m (in vigore dal aprile 2024, precedentemente 6 V/m).

- La posizione e la quota dei recettori sensibili (abitazioni, aree con permanenza prolungata) nel raggio significativo dalla torre.

Per Moricone questo passaggio è rilevante: la simulazione dovrà includere tutti gli impianti già presenti sul territorio, non solo la torre Inwit. Se da questa verifica emerge un superamento dei limiti, l'impianto non può essere acceso.

Fase 2 — Controlli post-installazione

L'operatore deve inviare al Comune e ad ARPA una Relazione ad impianto attivo con le caratteristiche radioelettriche effettive e misure presso i punti critici. ARPA verifica che l'impianto corrisponda alla configurazione autorizzata. I controlli successivi avvengono su piano annuale di attività di ARPA o su richiesta dei cittadini tramite il Comune.

La novità 2026: il catasto digitale di ARPA Lazio

A partire da aprile 2026 ARPA Lazio avvierà la piattaforma NirWeb/NirGis per il catasto regionale delle sorgenti elettromagnetiche. Prima di presentare una pratica di impatto elettromagnetico previsionale, il gestore dovrà accedere all'interfaccia NirWeb e inserire la scheda tecnica dell'impianto nel database, che genererà una ricevuta di registrazione da allegare alla documentazione. La pratica Inwit per Moricone entrerà quindi in questo sistema: è una buona notizia in termini di tracciabilità pubblica.

Cosa fa ARPA per legge vs. cosa deve garantire il contratto

Attività	Per legge (già garantita)	Da negoziare nel contratto
Parere preventivo prima dell'accensione	✅ Obbligatorio	—
Verifica post-installazione (relazione impianto attivo)	✅ Obbligatoria	—
Richiesta di misura su iniziativa del Comune	✅ Il Comune può attivare ARPA	Clausola: Inwit sostiene i costi della misura
Frequenza minima dei controlli periodici	❌ Dipende dal piano annuale ARPA	Clausola: misura ARPA almeno annuale con referto depositato al Comune
Misura strumentale di collaudo post-accensione	❌ Non automatica (solo relazione operatore)	Clausola: misura ARPA entro 60 gg dall'accensione
Nuova valutazione a ogni aggiunta di operatore	❌ Solo se l'operatore presenta nuova istanza	Clausola: ogni co-location attiva automaticamente nuova valutazione ARPA
Accesso pubblico ai risultati	❌ Dati nel catasto, non comunicati proattivamente	Clausola: trasmissione automatica al Comune e pubblicazione sul sito
Monitoraggio indipendente (non ARPA)	❌ Non previsto	Clausola: misura indipendente semestrale a carico Inwit
Aggiornamento dati NirWeb/NirGis al Comune	❌ Non automatico	Clausola: trasmissione dati catasto regionali contestualmente

		all'aggiornamento

Il punto critico: la co-location e le misurazioni cumulative

Questo è l'aspetto più sottovalutato. La normativa fissa i limiti sul campo elettromagnetico cumulativo di tutti gli impianti presenti, non del singolo. Quando Inwit aggiunge un secondo operatore anni dopo, ARPA effettuerà una nuova simulazione cumulativa — ma solo se viene presentata formalmente una nuova istanza. Il contratto dovrebbe prevedere esplicitamente che ogni aggiunta di operatore sulla torre attivi automaticamente una nuova valutazione ARPA, indipendentemente dalla soglia tecnica oltre la quale l'operatore sarebbe obbligato a presentarla autonomamente.

Questa clausola si integra direttamente con il vincolo parametrico descritto nella sezione 5.4-B: ogni variazione che supera uno dei tre parametri (potenza EIRP, numero operatori, ingombro fisico) genera automaticamente l'obbligo di nuova valutazione ARPA preventiva.

◆ VALUTAZIONE TECNICA

Le clausole di monitoraggio dovrebbero distinguere due livelli: (a) il monitoraggio ARPA istituzionale, che garantisce la conformità normativa, e (b) il monitoraggio indipendente a carico di Inwit, che garantisce la trasparenza verso i cittadini. Il secondo non è una duplicazione del primo: serve a fornire dati accessibili alla comunità senza dipendere dai tempi del piano annuale di ARPA.

Il contratto potrebbe prevedere che i risultati delle misure indipendenti semestrali siano pubblicati sul sito del Comune entro 30 giorni dalla loro effettuazione, e che in caso di superamento del valore di attenzione (15 V/m) scatti automaticamente una procedura di verifica urgente da parte di ARPA.

▲ ATTENZIONE

Il contratto dovrebbe essere valutato da un legale specializzato in diritto amministrativo e telecomunicazioni prima della firma. Le clausole di monitoraggio dovrebbero specificare con precisione chi commissiona le misure, chi le esegue, chi ne sostiene i costi, a chi vengono trasmessi i risultati e con quale tempistica. Clausole vaghe su questi punti non sono azionabili.

6. Cosa può e non può fare il Comune: il quadro normativo

6.1 Gli strumenti a disposizione

- Richiedere simulazione DTM reale come condizione pre-autorizzativa (art. 87 D.Lgs. 259/2003)
- Richiedere valutazione comparativa di siti alternativi prima della firma
- Imporre condizioni urbanistiche vincolanti: altezza massima, numero operatori, prescrizioni paesaggistiche
- Richiedere monitoraggio ARPA periodico con pubblicazione pubblica

- Negoziare canone equo e condizioni contrattuali favorevoli
- Adottare un regolamento antenne ex art. 8 c.6 L. 36/2001 se non già esistente

6.2 I limiti da rispettare

- Non si possono imporre distanze minime obbligatorie dalle abitazioni: illegittimo per giurisprudenza consolidata del Consiglio di Stato
- Non si può bloccare il progetto invocando rischi sanitari non documentati
- il D.L. 60/2024 conv. in L. 95/2024 (art. 4, comma 7-bis) consente installazioni in deroga ai regolamenti comunali per le aree bianche PNRR: un'opposizione frontale sarebbe perdente

6.3 I precedenti giurisprudenziali più rilevanti

TAR Lombardia Brescia, Ord. 266/2025 – ogni parere negativo deve indicare soluzioni alternative. Il Comune che propone siti alternativi motivati tecnicamente è nella posizione giuridicamente più forte.

TAR Lecce 2024, Martina Franca / Inwit – annullata un'autorizzazione perché Inwit aveva ignorato il regolamento comunale sulla valutazione di siti alternativi. Se Moricone adotta un regolamento antenne, Inwit è tenuta a rispettarlo.

Comune di Fano, ottobre 2024 – il Comune ha proposto più siti alternativi, Inwit li ha rifiutati tutti. Il sindaco: 'non esistono strumenti per fermare l'opera'. La leva principale rimane il contratto.

Consiglio di Stato, sentt. 5283 e 5629/2022 – i regolamenti comunali possono definire criteri localizzativi specifici, non divieti generalizzati che impediscano la copertura del territorio.

7. Approfondimento tecnico: mappe, pixel e analisi radio

7.1 La mappatura Infratel: come leggere i colori

La mappa ufficiale Infratel 2024 divide il territorio in pixel colorati, ciascuno con un significato preciso. È importante capire questa distinzione perché solo i pixel viola rientrano nel mandato PNRR di Inwit.

Tipo	Cosa c'è dentro	Colore mappa	Chi interviene
Tipo 2	Aree urbane con abitazioni	Rosa chiaro	Intervento PRIVATO degli operatori telefonici
Tipo 6	Aree agricole con presenza umana	Viola	Piano Italia 5G – finanziamento PNRR
Tipo 7	Strade, boschi, aree non abitate	Viola	Piano Italia 5G – finanziamento PNRR

Fig. 3 – Legenda ufficiale Infratel 2024. Solo il colore viola identifica le 'Aree interessate dal Piano Italia 5G' coperte con fondi PNRR. Le altre categorie sono soggette a intervento privato. Fonte: Infratel Italia.

7.2 I pixel di Moricone: fonte ufficiale

I pixel del Piano Italia 5G assegnati al Comune di Moricone sono consultabili nel CSV ufficiale dell'Allegato A, disponibile al seguente indirizzo:
https://storymaps.arcgis.com/stories/86240a909c5b49b591ba5649aba7d1dd

7.3 L'analisi della linea di vista (LOS)

L'analisi seguente è riferita al sito dell'ecocentro comunale (42.111788°N, 12.762149°E, quota 182 m s.l.m.), individuato dalla delibera del 5 marzo 2026 come posizione per la torre.

Per verificare se la torre può 'vedere' i pixel della zona bianca, è stato usato HeyWhatsThat Path Profiler (SRTM 30m, Terra curva, rifrazione k=0.14, 700 MHz). Lo strumento disegna il profilo del terreno tra due punti e mostra se ci sono ostacoli che interrompono il segnale radio.

I grafici seguenti mostrano i due percorsi estremi: verso il pixel più a nord (~1 km) e verso quello più a sud (~1,2 km). Le linee rosse indicano i limiti della zona di Fresnel, il volume entro cui il segnale deve potersi propagare liberamente.

Percorso verso il pixel SS636 nord (~1,0 km)

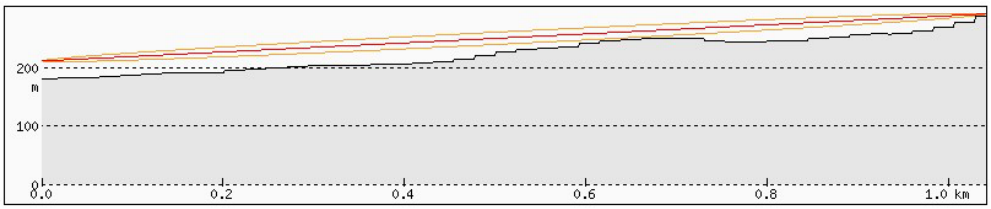

Fig. 5a – Profilo altimetrico Ecocentro → pixel SS636 nord. Il terreno sale gradualmente, la zona di Fresnel (tra le due linee rosse) rimane libera: LOS libera. Fonte: HeyWhatsThat.com, SRTM 30m.

Percorso verso il pixel SS636 sud (~1,2 km)

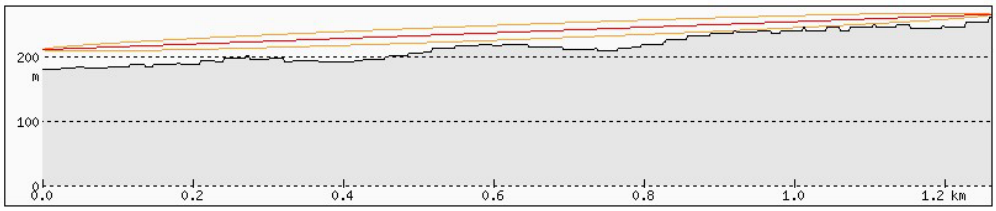

Fig. 5b – Profilo altimetrico Ecocentro → pixel SS636 sud. Anche in questo caso LOS geometrica libera. Il dislivello tra la cima torre (212 m) e il pixel (259 m) è chiaramente visibile. Fonte: HeyWhatsThat.com, SRTM 30m.

✓ VALUTAZIONE PRELIMINARE

I profili altimetrici basati su dati SRTM 30m indicano linea di vista geometricamente libera verso entrambi i pixel estremi della zona bianca. La copertura appare geometricamente plausibile sulla base di questa analisi preliminare. Il dislivello sfavorevole tra la cima torre (212 m) e i pixel target (259–287 m) è reale e richiede verifica con simulazione DTM professionale per stabilire l'altezza minima effettiva.

8. Accesso agli atti: i diritti dei cittadini

In base al D.Lgs. 33/2013, art. 5 comma 2 (accesso civico generalizzato) e agli artt. 22 e ss. della L. 241/1990 (accesso documentale), ogni cittadino può richiedere formalmente al Comune di Moricone:

- Tutta la corrispondenza intercorsa tra Comune e Inwit dall'avvio dell'iter (luglio 2025) ad oggi
- La proposta contrattuale inviata da Inwit e la controproposta del Sindaco (febbraio 2026)
- La delibera del 5 marzo 2026 e gli atti istruttori che l'hanno preceduta
- Eventuali perizie o valutazioni tecniche commissionate o ricevute
- Il parere ARPA, se già richiesto in fase istruttoria

Il Comune ha 30 giorni per rispondere. In caso di silenzio o diniego immotivato: ricorso al RPCT (Responsabile Prevenzione Corruzione e Trasparenza) del Comune o, in extremis, al TAR.

9. Riepilogo

	Elemento	Cosa significa
F	Pixel viola lungo SS636: strade e aree rurali, non il centro abitato	Il bando PNRR riguarda la SS636, non necessariamente il paese
F	Ecocentro a 182 m, pixel target tra 259 e 287 m s.l.m.	Dislivello fino a 105 m: elemento che merita verifica tramite simulazione DTM professionale

F	LOS geometrica libera verso entrambi i pixel estremi	Copertura plausibile ma non dimostrata: serve simulazione DTM
F	Delibera approvata il 5 marzo 2026, contratto non ancora firmato (la delibera non era ancora disponibile nell'albo pretorio al momento della redazione)	La finestra negoziale è ancora aperta: usarla prima della firma
?	Punto di attestazione del backhauling FiberCop non noto	Potrebbe cambiare la preferenza di Inwit per il sito: da chiarire prima della firma
?	Simulazione DTM non ancora depositata agli atti	L'altezza minima effettiva non è ancora verificata: potrebbe essere >30 m
◆	Sito comunale ottimizzato per la copertura del paese aumenta l'attrattività per la co-location	Il contratto deve limitare altezza e numero di operatori per proteggere il territorio nel tempo
▲	Il contratto avrà durata pluriennale con opzione di rinnovo (secondo quanto riferito nel colloquio del 4 marzo 2026, non ancora firmato): le clausole di oggi sono vincolanti a lungo	Valutazione legale della bozza contrattuale prima della firma è imprescindibile

Legenda: F = Fatto accertato | ? = Elemento da verificare | ◆ = Valutazione tecnica | ▲ = Attenzione

10. Fonti e riferimenti

Dati ufficiali e mappe

- Infratel Italia, Mappatura Mobile 2024: https://infratelitalia.maps.arcgis.com/apps/webappviewer/index.html?id=31edaac5b99c44e6828c6cd365792e2c
- Piano Italia 5G, Allegato A (CSV pixel per regione): https://storymaps.arcgis.com/stories/86240a909c5b49b591ba5649aba7d1dd
- Stato piani PNRR per comune: https://connetti.italia.it
- Profili altimetrici e LOS: HeyWhatsThat.com (SRTM 30m, Terra curva, k=0.14, 700 MHz)
- Coordinate e quote: Google Maps / Google Earth (WGS84 gradi decimali)

Normativa di riferimento

- Legge 22 febbraio 2001 n. 36, art. 8 c.6 – Regolamento comunale antenne
- D.Lgs. 1 agosto 2003 n. 259, artt. 86–87 – Codice Comunicazioni Elettroniche: autorizzazione impianti e simulazione DTM
- D.L. 7 maggio 2024 n. 60, conv. in L. 4 luglio 2024 n. 95, art. 4, comma 7-bis -- Deroga ai regolamenti comunali per aree bianche PNRR
- D.Lgs. 14 marzo 2013 n. 33, art. 5 comma 2 -- Accesso civico generalizzato
- Legge 7 agosto 1990 n. 241, artt. 22 e ss. -- Accesso documentale (richiede interesse diretto, concreto e attuale)
- Legge 7 agosto 1990 n. 241, art. 22 – Accesso agli atti amministrativi

Giurisprudenza

- TAR Lombardia Brescia, Ord. n. 266/2025 – obbligo di indicare soluzioni alternative nel diniego
- Consiglio di Stato, sentt. n. 5283 e 5629/2022 – limiti del regolamento comunale antenne
- TAR Lecce 2024 – annullamento autorizzazione Inwit per violazione regolamento comunale
- Corte Costituzionale n. 307/2003 e 331/2003 -- illegittimità limitazioni distanziali generalizzate

Casi analoghi

- Comune di Fano – siti alternativi proposti e rifiutati da Inwit (ottobre 2024)
- Comune di Terni, Collepaese -- torre Inwit 36 m (novembre–dicembre 2025) https://www.umbriaon.it
- Comune di Martina Franca – TAR Lecce annulla autorizzazione Inwit: https://www.valleditrianews.it

---

Documento redatto nel marzo 2026 su dati pubblici ufficiali. Non costituisce parere legale.

Il presente documento è stato redatto da un cittadino residente nel Comune di Moricone sulla base di dati e fonti pubbliche disponibili: documentazione ufficiale Infratel Italia, normativa di settore, cartografia territoriale, atti e delibere comunali pubblicamente accessibili. L'analisi ha finalità esclusivamente informative e divulgative per la comunità locale e non costituisce una perizia tecnica, un parere professionale né un atto giuridico di alcun tipo. Le valutazioni di natura radioelettrica e territoriale hanno carattere preliminare e orientativo: la verifica definitiva compete agli operatori e agli enti tecnici competenti nell'ambito dei procedimenti autorizzativi previsti dalla normativa vigente. L'autore risiede nel Comune di Moricone con la propria abitazione a circa 200 metri dall'area dell'ecocentro e ha quindi un interesse diretto nella questione trattata. Non ha interessi economici né rappresenta associazioni, comitati o gruppi politici. Pur avendo verificato i riferimenti normativi, giurisprudenziali e fattuali sulla base di fonti pubbliche disponibili al momento della redazione, il documento potrebbe contenere inesattezze o essere superato da sviluppi successivi: il lettore è invitato a verificare autonomamente le informazioni prima di farne uso in sede amministrativa o legale.

Lorenzo Moretti
Cittadino residente nel Comune di Moricone
Marzo 2026